TIQUES ET PAYSAGES EN FRANCE

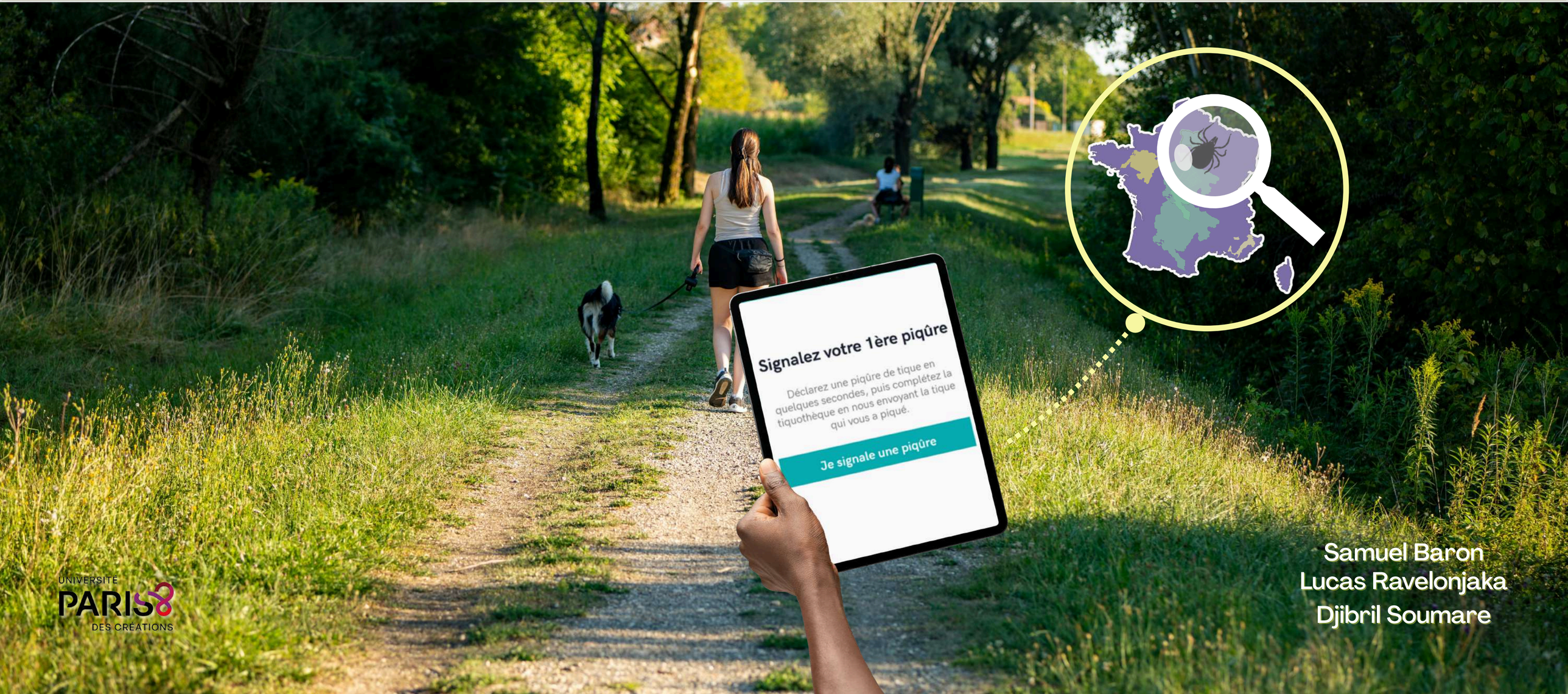

Samuel Baron
Lucas Ravelonjaka
Djibril Soumare

UNIVERSITÉ PARIS 8 DES CRÉATIONS

Objectif : Identifier et de cartographier les profils paysagers associés aux zones de signalements de piqûres de tique

Un risque mal défini spatialement...

Environ 100 000 signalements depuis 2017.
Mais lien flou avec des types de paysages.

Données mobilisées

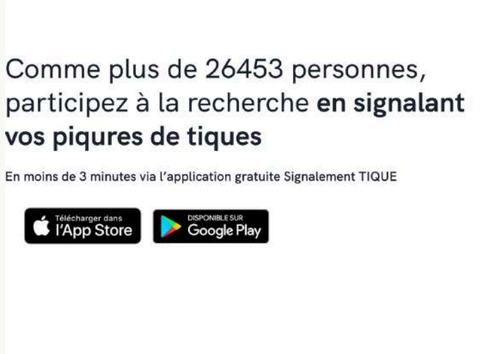

Données CITIQUE 2017-2020, INRAE
2,289 piqûre sur des chiens

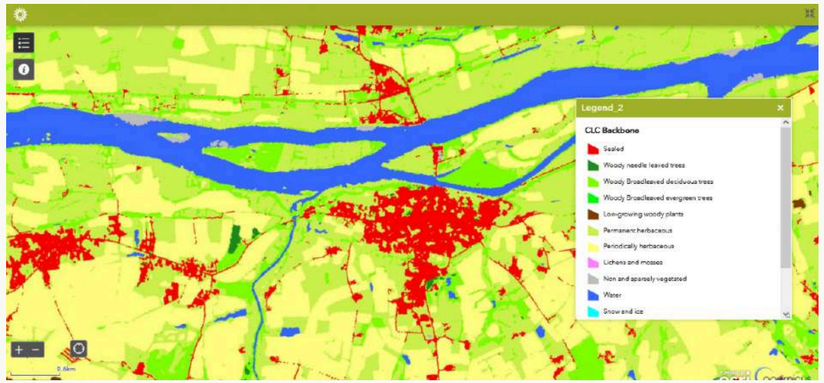

CLC+ Backbone 2018, Copernicus, AEE
Occupation du sol

MÉTHODE

Feuille de route :

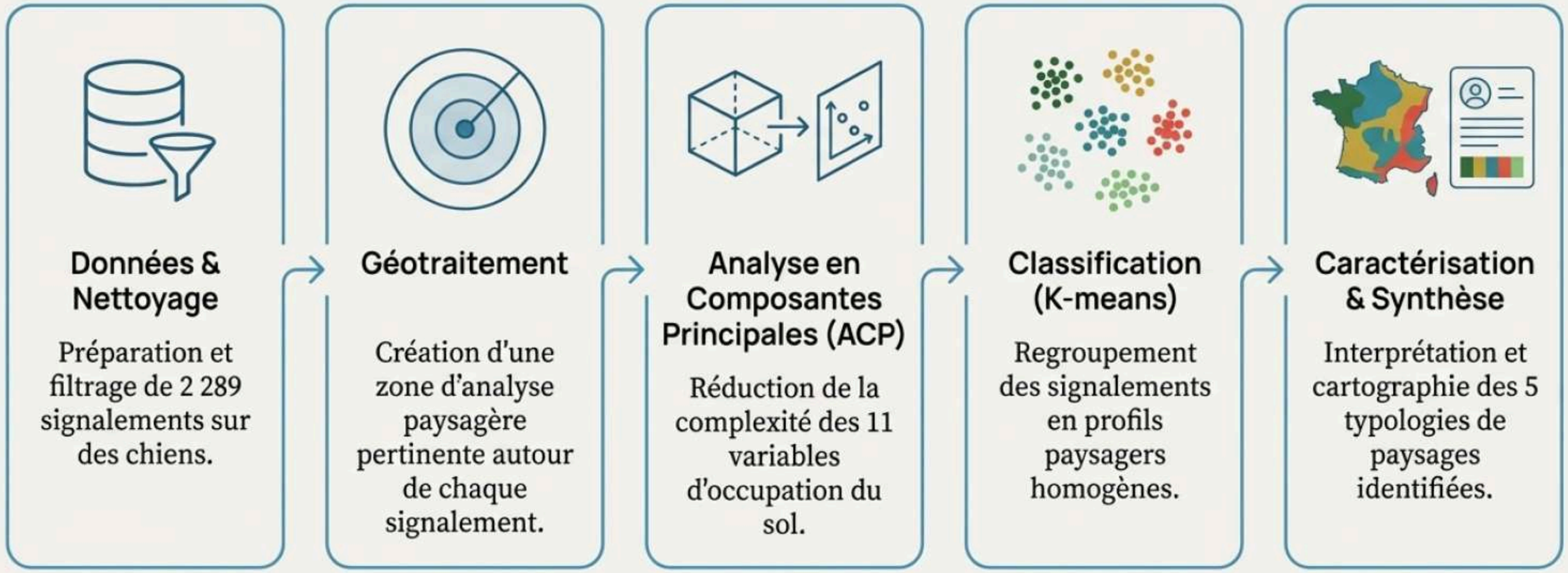

Outils :

1. Définition d'un rayon d'analyse autour des signalements

Distribution fortement asymétrique

70% des piqûres : inferieur à 2,36km

Médiane : 0,83km

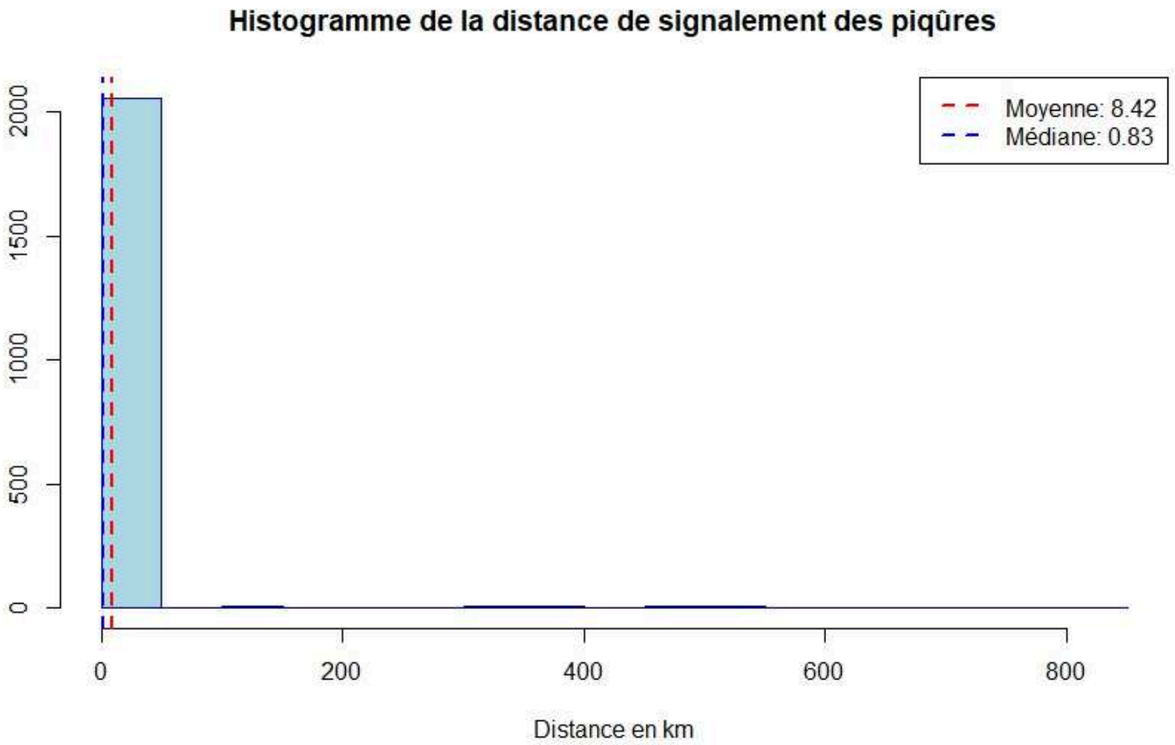

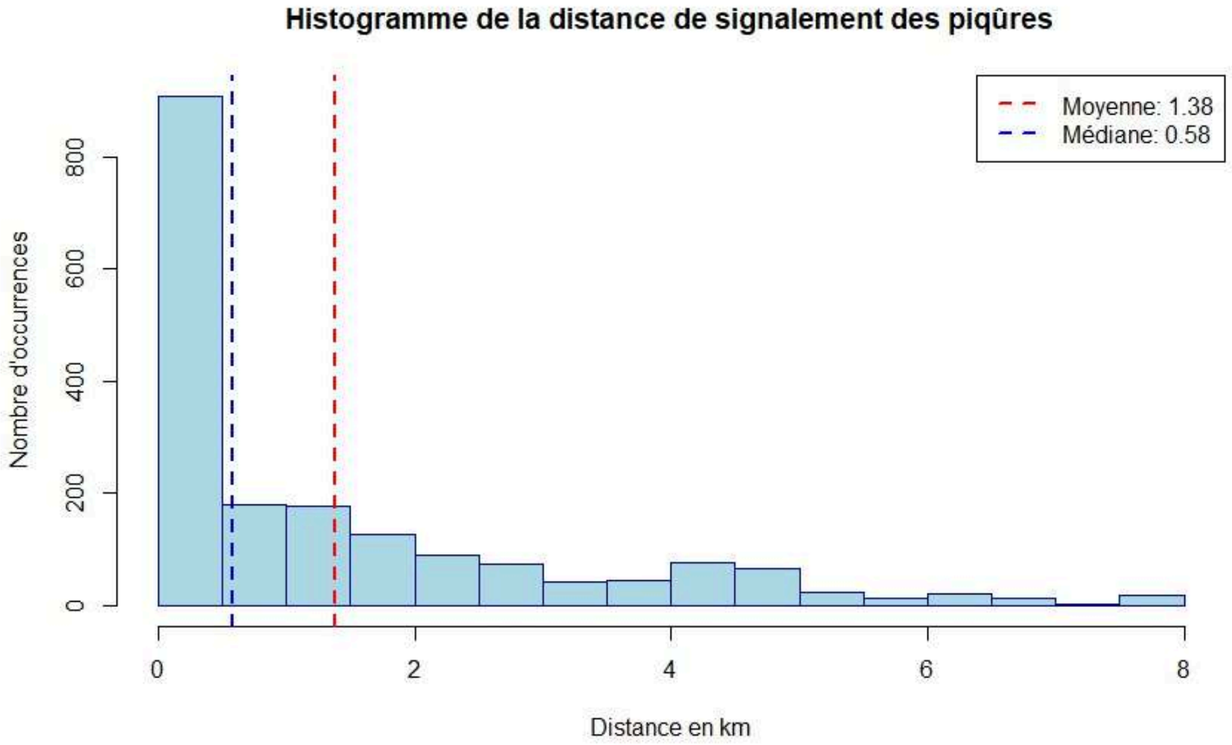

Valeurs extrêmes jusqu'à 834km

Moyenne sur 90% des distances : 1,3km

2. Statistiques descriptives

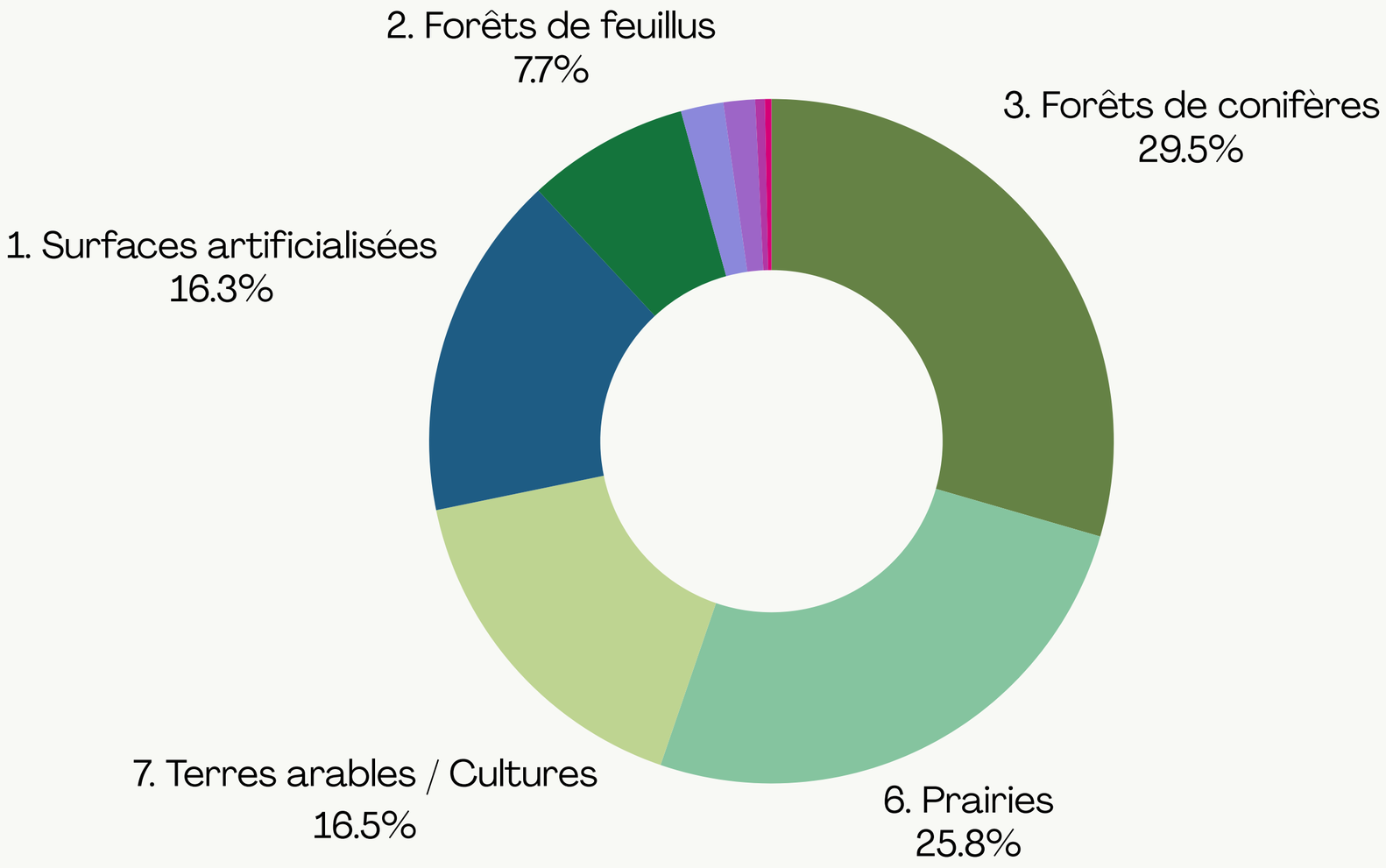

Répartion des principales classes d'occupation du sol autour des signalements (1,3km)

3. ACP

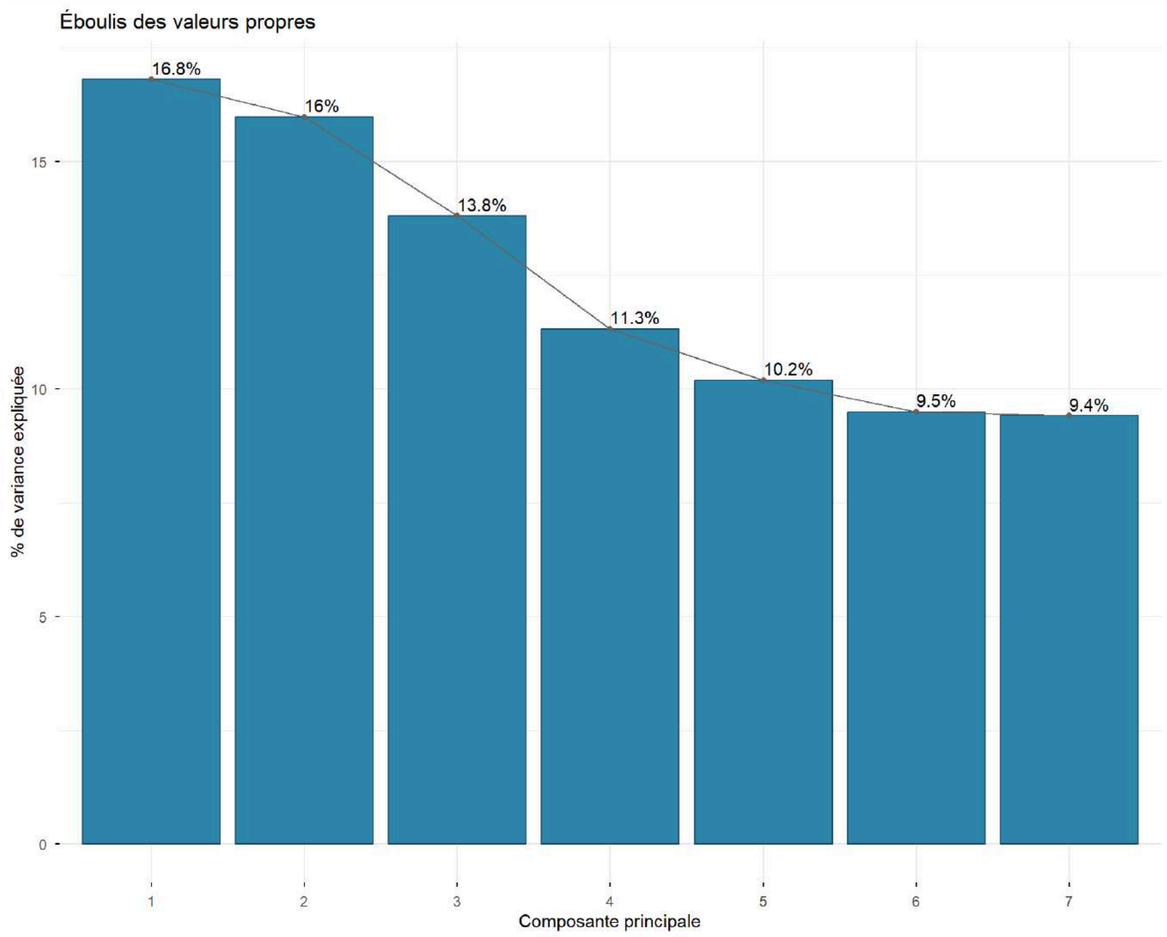

Répartition de la variance expliquée par les axes de l'ACP

Axe	Nom du gradient	Pôle 1	Pôle 2
Axe 1	Naturalité vs Agriculture	Milieux naturels boisés	Espaces agricoles ouverts
Axe 2	Forêt vs Anthropisation	Forêts (feuillus / conifères)	Agricole & urbain
Axe 3	Complexité naturelle	Milieux naturels hétérogènes	Artificialisation
Axe 4	Littoral	Espaces marins	Milieux humides et ouverts
Axe 5	Maritimité	Environnement marin	Agriculture intérieure

Les gradients d'occupation du sol issus de l'ACP

4. Classification K-means

Détermination du nombre optimal de clusters

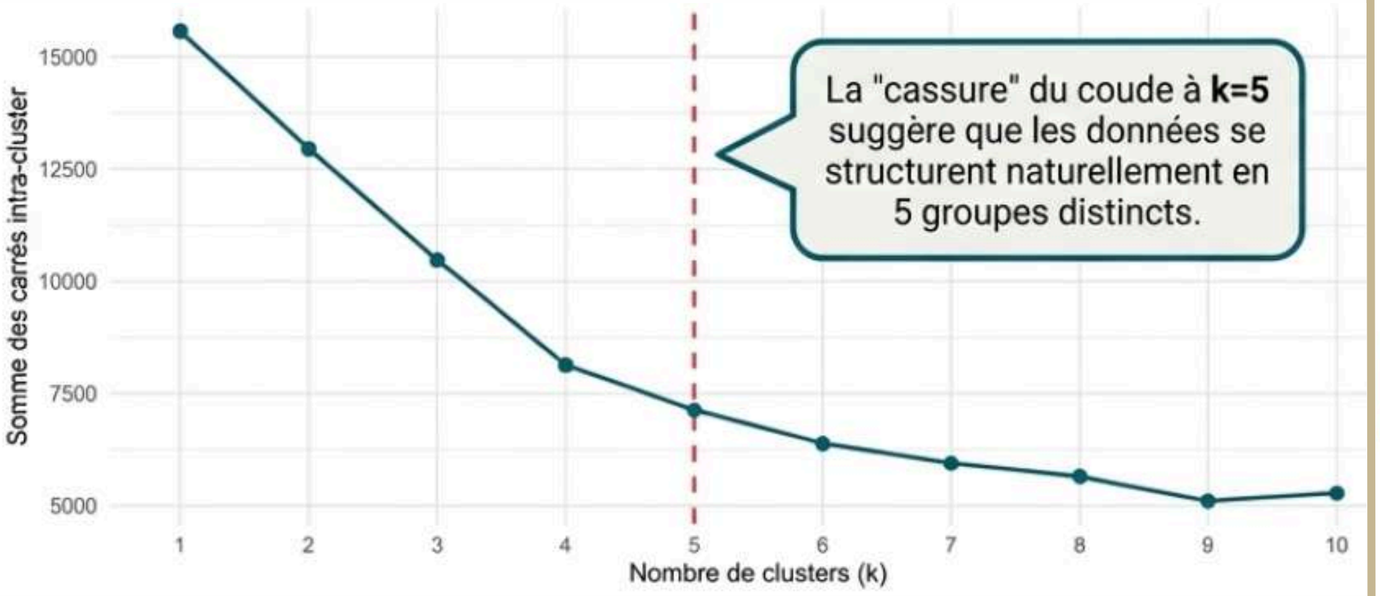

Les gradients d'occupation du sol issus de l'ACP

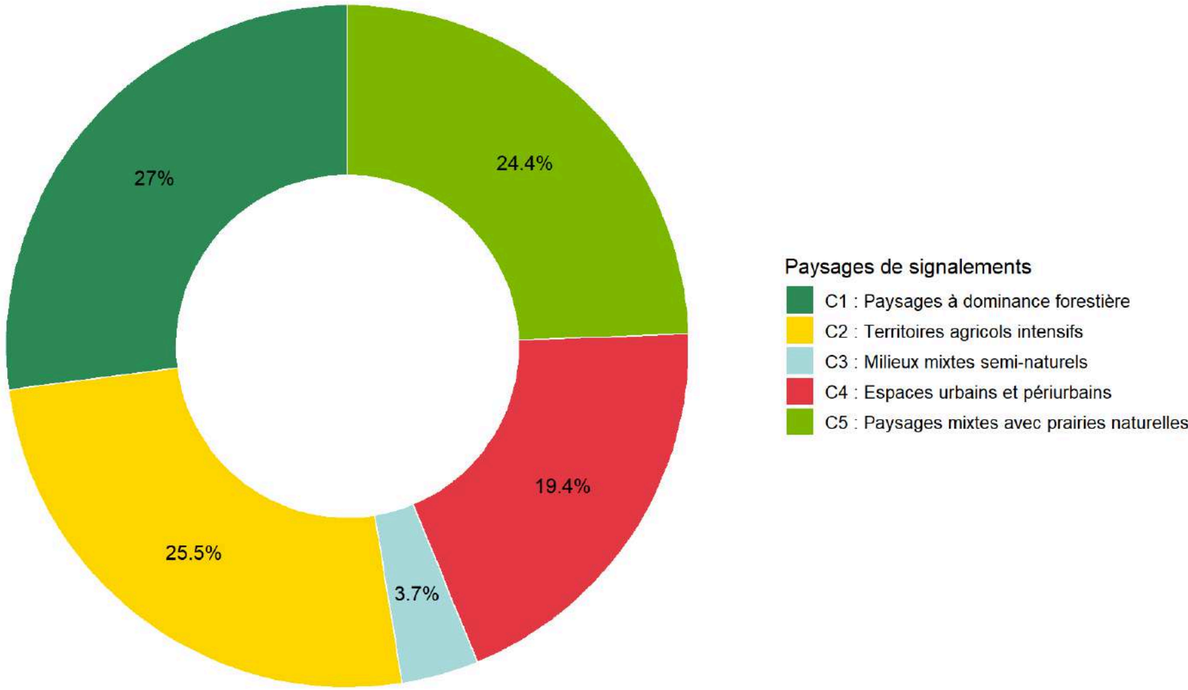

La classification confirme la structure révélée par l'analyse en composantes principales.

Le cluster **urbain/périurbain** se positionne sur le pôle anthropisé des axes.

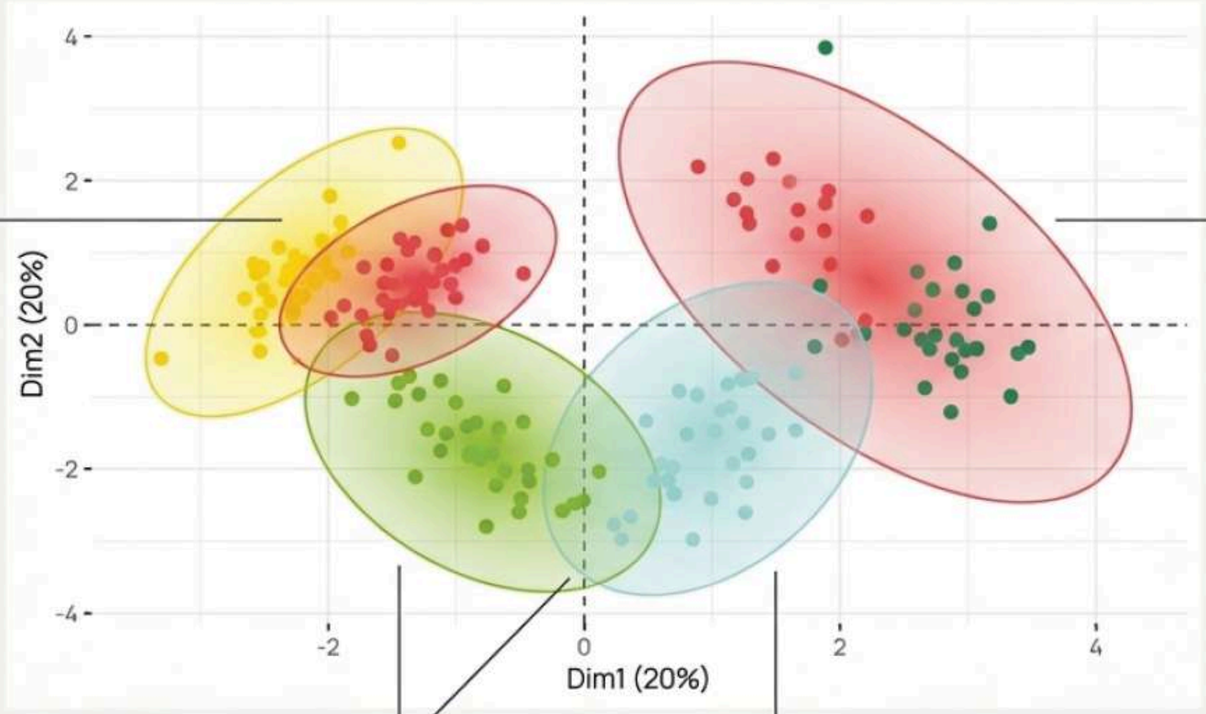

Le cluster **forestier** est fortement influencé par le pôle naturel/boisé.

Les clusters **agricole** et **prairial** se distinguent le long de l'axe 1 (Agricole/Cultivé).

- C1 : Forestier
- C2 : Agricole
- C3 : Semi-naturel
- C4 : Urbain
- C5 : Prairial

RÉSULTAT

Typologies paysagères des signalements de piqûres de tiques sur les chiens (2017-2021)

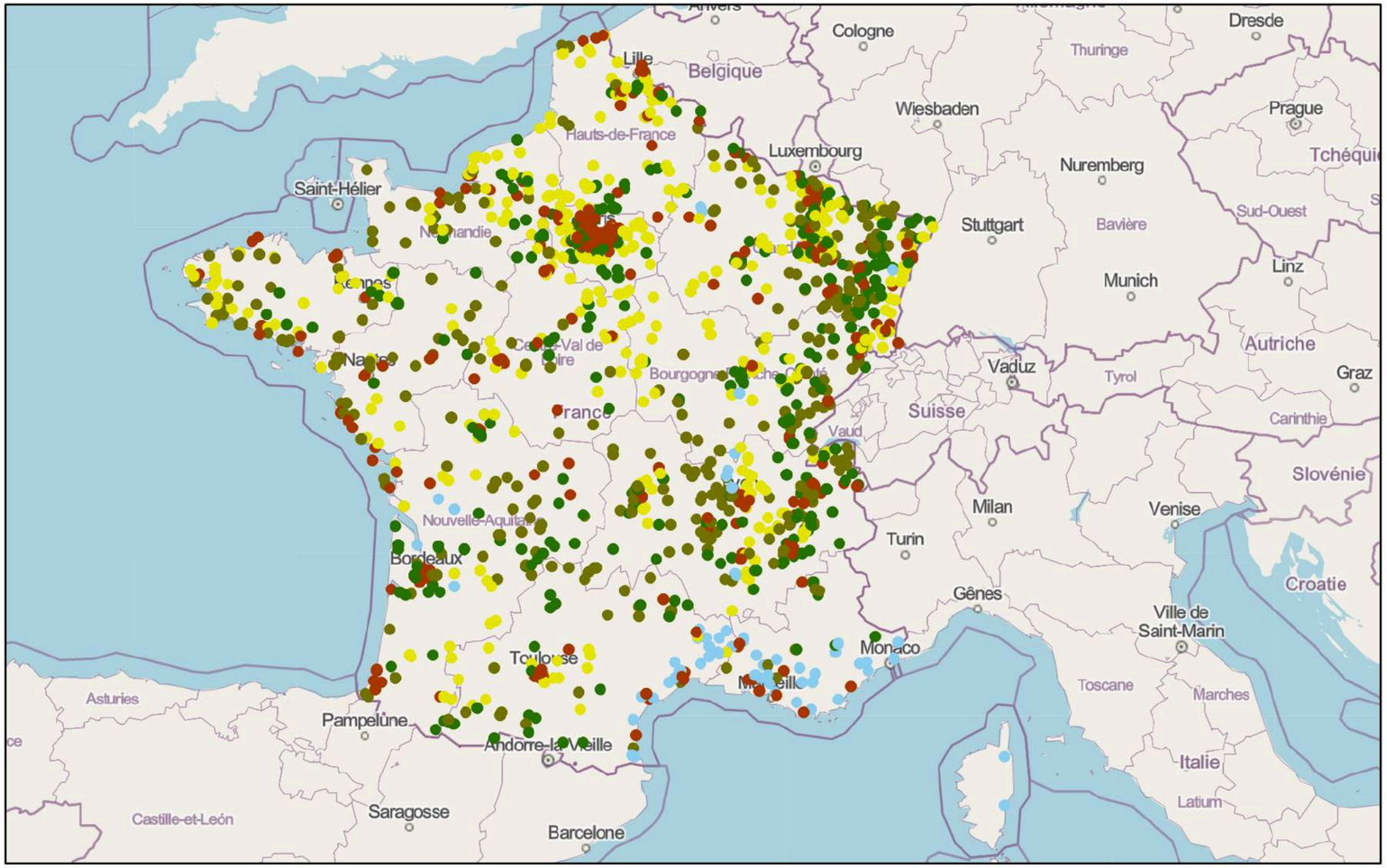

08/01/2026

Typologie paysagère

- C1 : Paysages à dominance forestière
- C2 : Territoires agricols intensifs
- C3 : Milieux mixtes semi-naturels
- C4 : Espaces urbains et périurbains
- C5 : Paysages mixtes avec prairies naturelles

1:10,400,251

0 60 120 240 mi

0 95 190 380 km

Map data © OpenStreetMap contributors, Microsoft, Facebook, Google, Esri Community Maps contributors, Map layer by Esri

Groupe B, projet tutoré

CONCLUSION

- Les piqûres de tiques s'inscrivent dans des paysages variés et souvent mixtes, à l'interface entre milieux naturels, agricoles et anthropisés.

- Les analyses multivariées permettent de structurer cette diversité en gradients et typologies paysagères interprétables.

- L'approche est pertinente mais dépendante des biais liés aux données participatives et aux choix méthodologiques (buffers, classification).

- Ces résultats décrivent des contextes paysagers de signalement, et ouvrent la voie à des analyses spatio-temporelles et à l'intégration de variables complémentaires.

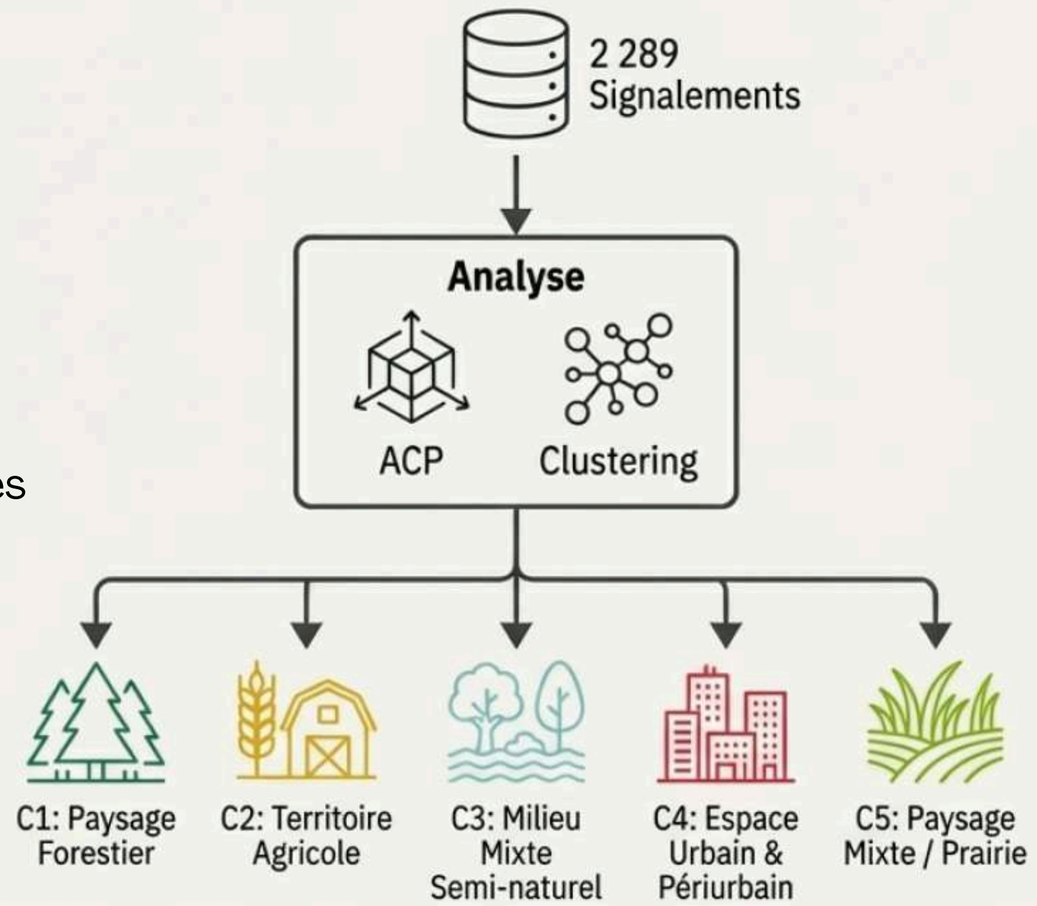

TIQUES ET PAYSAGES EN FRANCE

MERCI !

Remerciement spéciale :

M. V. Godard & E. Delmelle pour le guidage et l'encadrement

UNIVERSITÉ PARIS 8 DES CRÉATIONS

Samuel Baron
Lucas Ravelonjaka
Djibril Soumare

Photo de Vladimir Srajber
https://www.pexels.com/fr-fr/photo/femme-promenant-son-chien-sur-un-sentier-forestier-ensoleille-33839705/